Geom. Rudy Manenti
mob. +39 392 1649505
mail: manenti.rudy@gmail.com
via Valmarana, 81 - 30034 Mira (VE)
C.F. MNNRDY89S13L736L
P.Iva 04704830274
www.volarealto.biz

Geom. Diego Bacci
mob. +39 351 544 7413
mlservizi13@gmail.com
Via Banchina dell'azoto, 15 - 30175 Venezia (VE)
C.F.: BCCDGI72T01L736I
P.iva: IT 03775220274
www.mlservizivenezia.com

Presentazione

Dal 2019, la collaborazione sinergica tra il geom. Manenti Rudy della ditta Volare Alto e il geom. Bacci Diego della ditta ML Servizi si è consolidata nel fornire servizi tecnici di eccellenza nel vasto campo dell'edilizia, sfruttando le potenzialità innovative offerte dall'utilizzo dei droni. La nostra lunga e preziosa esperienza, unita a una profonda conoscenza di una disciplina in continua evoluzione, ci consente di abbracciare un ampio spettro di attività, che variano dalle ispezioni di base alla restituzione tridimensionale di modelli di edifici complessi.

Il nostro cammino professionale ci ha guidato verso l'adozione di droni dotati di fotocamere multispettrali, in grado di acquisire dati sulle bande del Vicino-infrarosso (NIR), Red edge (RE), Rosso (R), Verde (G), oltre alla visibile RGB. Questi strumenti avanzati, impiegati con successo nel rilievo di coltivazioni, ci consentono di generare mappe georeferenziate basate su indici che rivelano la vigoria delle piante, come ad esempio il noto NDVI, identificando lo stress idrico e la presenza di clorofilla.
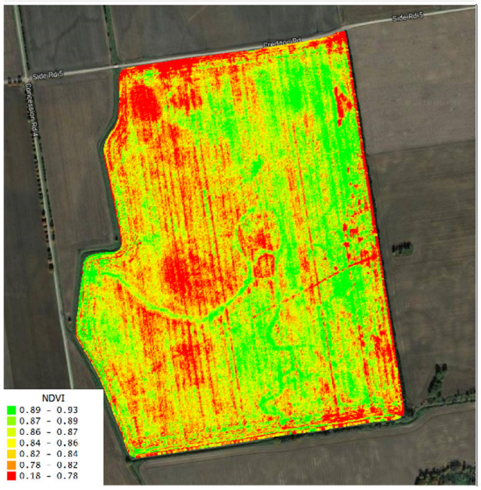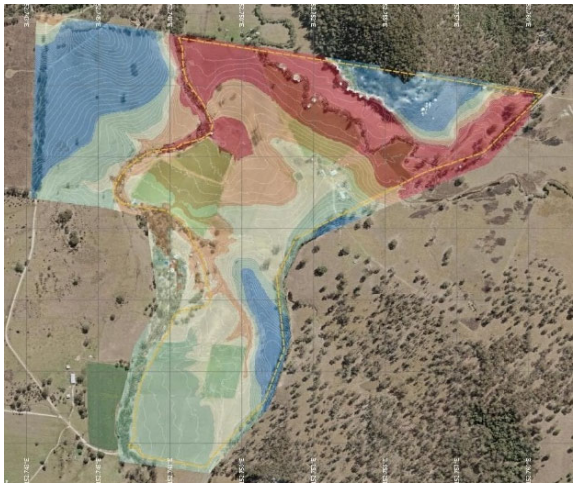
Le immagini catturate attraverso le fotocamere RGB, sottoposte a un'elaborazione accurata, si trasformano in mappe georeferenziate ad altissima definizione. Queste risultano estremamente utili per individuare smottamenti del terreno o per ottenere immagini di facile interpretazione riguardo all'andamento planimetrico del suolo. Questo aspetto risulta fondamentale per lo studio approfondito dello scorrimento dell'acqua e per una comprensione dettagliata del contesto ambientale in cui interveniamo.