Geom. Diego Bacci
mob. +39 351 544 7413
mlservizi13@gmail.com
Via Banchina dell'azoto, 15 - 30175
Venezia (VE)
C.F.: BCCDGI72T01L736I
P.iva: IT 03775220274
www.mlservizivenezia.com

Presentazione

Il Geom. Bacci Diego della ditta ML Servizi ha consolidato la propria esperienza maturata negli anni e ha inizio nel 2019. Nel vasto campo dell'edilizia offro molteplici servizi tecnici di eccellenza, sfruttando le potenzialità innovative legate all'utilizzo di droni di alta qualità.

La passione nell'approfondire le diverse tematiche di una disciplina in continua evoluzione mi ha permesso di ampliare le conoscenze tecniche necessarie per svolgere attività di diverso tipo, come ispezioni di base e restituzioni tridimensionali di modelli di edifici complessi.

L'utilizzo dei droni per effettuare i rilievi topografici hanno molteplici vantaggi in termini di efficienza e sicurezza, precisione e risparmio dei costi. Ad esempio, i droni possono coprire grandi aree in tempi brevi, consentendo di acquisire i dati in modo rapido e preciso. Possono accedere a zone pericolose per gli operatori, come i tetti, i tralicci o le aree boschive. È indubbia l'elevata precisione nell'acquisizione dei dati grazie all'utilizzo dei droni che consentono di creare modelli 3D dettagliati e realistici, riducendo i costi di rilievo rispetto ai metodi tradizionali.

I Geom. Bacci dispone di attrezzature all'avanguardia e di software di ultima generazione per soddisfare le esigenze di ciascun cliente che richieda un servizio completo e personalizzato.

Applicazioni

Studi professionali, topografi ed imprese possono richiedere il loro servizio tra alcune delle principali applicazioni.

RILIEVI TOPOGRAFICI

- Creazione di modelli 3D di terreni, edifici e infrastrutture con DTM (Digital Terrain Model) e DSM (Digital Surface Model) ad alta risoluzione
- Calcolo di volumi e superfici
- Rilievi planimetrici e altimetrici
- Rilievi di dettaglio per la progettazione di opere civili e infrastrutture
- Monitoraggio di dissesto del terreno e frane

ORTOFOTO

- Fotografie aeree ad alta risoluzione (fino a 5 cm/pixel) con georeferenziazione
- Ortofoto mosaici per la creazione di mappe e planimetrie
- Riprese aeree oblique per la valorizzazione di edifici e paesaggi

ISPEZIONI

- Ispezioni di ponti, viadotti, edifici e altre infrastrutture con immagini ad alta risoluzione e video
- Rilevazione di crepe, fessurazioni e altri ammaloramenti
- Ispezioni di tetti, coperture e canne fumarie

Geom. Diego Bacci
mob. +39 351 544 7413
mlservizi13@gmail.com
Via Banchina dell'azoto, 15 - 30175
Venezia (VE)
C.F.: BCCDGI72T01L736I
P.iva: IT 03775220274
www.mlservizivenezia.com

Selezione di alcuni lavori svolti

Tempio Canoviano di Possagno (TV)

Rilievo misto laser scanner, drone e palina GNSS del Tempio Canoviano di Possagno. Restituzione di modello BIM e piano quotato

Dolo (VE)

Rilievo delle facciate del Duomo di Dolo con utilizzo di GCP e restituzione di ortofoto con GSD minore di 0,4 cm/pixel e modello BIM. Rilievo finalizzato ad un restauro

Geom. Diego Bacci
mob. +39 351 544 7413
mlservizi13@gmail.com
Via Banchina dell'azoto, 15 - 30175
Venezia (VE)
C.F.: BCCDGI72T01L736I
P.iva: IT 03775220274
www.mlservizivenezia.com

Villa – Lido di Venezia (VE)

Rilievo misto laser scanner e drone di un immobile presso il Lido di Venezia





Gorgo al Monticano (TV)

Rilievo di condomino con utilizzo di GCP e scale bar, restituzione di nuvola di punti e modello 3D BIM. Rilievo finalizzato ad una riqualificazione energetica

Geom. Diego Bacci
mob. +39 351 544 7413
mlservizi13@gmail.com
Via Banchina dell'azoto, 15 - 30175
Venezia (VE)
C.F.: BCCDGI72T01L736I
P.iva: IT 03775220274
www.mlservizivenezia.com

Venezia

Rilievo di fabbricato nel centro storico di Venezia con utilizzo di GCP e scale bar, restituzione di nuvola di punti e prospetti 2D. Rilievo finalizzato ad un restauro. Autorizzazione acquisita per volo in zona LI-P

Cavarzere (VE)

Rilievo di manufatto storico con utilizzo di GCP e integrazione di dati con laser scanner per successivi lavori di restauro



Geom. Diego Bacci
mob. +39 351 544 7413
mlservizi13@gmail.com
Via Banchina dell'azoto, 15 - 30175
Venezia (VE)
C.F.: BCCDGI72T01L736I
P.iva: IT 03775220274
www.mlservizivenezia.com

Mirano (VE)

Rilievo di fabbricato residenziale con utilizzo di GCP e scale bar, restituzione di nuvola di punti e modello 3D BIM per lavori di ristrutturazione

Venezia

Monitoraggio settimanale delle strade adiacenti ad un cantiere sito presso l'isola del Tronchetto - Venezia, per il monitoraggio dei cedimenti mediante restituzione di ortofoto. Integrazione GCP con coordinate acquisite dal cliente. Autorizzazione acquisita per volo in zona LI-P. GSD 0,5 cm/pixel



Geom. Diego Bacci
mob. +39 351 544 7413
mlservizi13@gmail.com
Via Banchina dell'azoto, 15 - 30175
Venezia (VE)
C.F.: BCCDGI72T01L736I
P.iva: IT 03775220274
www.mlservizivenezia.com

Bibione (VE)

Il complesso dell'ex Colonia Femminile di Bibione è inserito all'interno di una pineta di circa 40.000 mq ed è composto da undici fabbricati di varie dimensioni e destinazioni. L'area si configura come un compendio unitario di rilevante valore architettonico e storico, caratterizzato da edifici a sviluppo pluripiano immersi nel contesto naturale costiero.

PADIGLIONE PRINCIPALE:

Il padiglione principale rappresenta l'edificio di maggiore rilevanza del complesso. Si sviluppa su più livelli (interrato, terra, primo, secondo, terzo, sottotetto e copertura) per una superficie complessiva di circa 12.000 mq. L'impianto planimetrico è articolato, con prospetti caratterizzati da una scansione regolare delle aperture e da volumi accessori al piano terra. I rilievi sono stati eseguiti internamente mediante laser scanner ed esternamente tramite drone, con restituzione digitale dell'intero edificio.

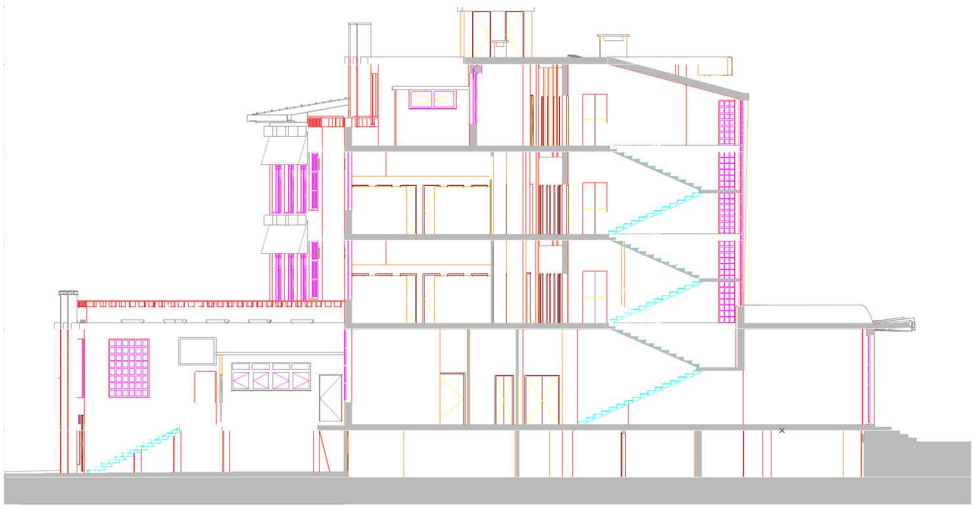

Geom. Diego Bacci
mob. +39 351 544 7413
mlservizi13@gmail.com
Via Banchina dell'azoto, 15 - 30175
Venezia (VE)
C.F.: BCCDGI72T01L736I
P.iva: IT 03775220274
www.mlservizivenezia.com

EX CINEMA:
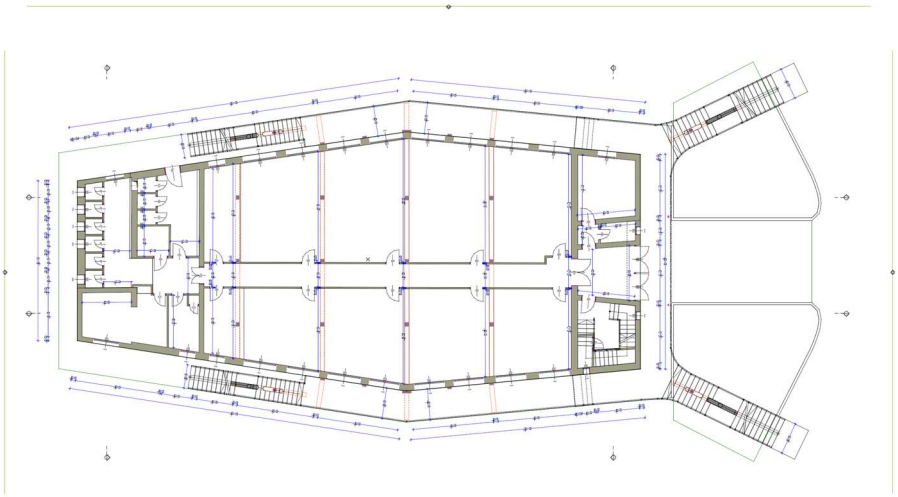
L'edificio denominato "Ex Cinema" costituisce uno dei fabbricati accessori del complesso ed è caratterizzato da un volume autonomo con copertura curva e ampia sala interna a doppia altezza. Il fabbricato presenta spazi destinati originariamente ad attività collettive e ricreative, con accessi indipendenti e collegamenti esterni mediante rampe e scale.